5812

विक्रय – पत्र

(वांछित–विवरण)

विक्रय मूल्य	:	70,00,000/– रूपये
बाजारी मूल्य	:	70,00,000/– रूपये
ई–स्टाम्प	:	***E- Stamp Attached***
स्टाम्प शुल्क	:	3,50,500/– रूपये
सर्किल रेट	:	7000/– रूपये प्रति वर्गमीटर
स्थित मौजा	:	धौलास
मुख्य चकराता रोड से दूरी	:	8 किमी0 से अधिक दूरी पर स्थित
विक्रीत कुल रकबा	:	947.80 वर्गमीटर
किस्म भूमि	:	आवासीय

श्री राजेश कुमार बेलवाल पुत्र श्री रामचन्द्र बेलवाल निवासी– एकता विहार सहस्त्रधारा रोड देहरादून, उत्तराखण्ड।
PAN-AJHPB5778N

..... विक्रेता

श्री श्याम कुमार गुजराल पुत्र श्री बी0एन0 गुजराल निवासी–79/14 मुनिसिपल रोड डालनवाला जिला देहरादून।
PAN-ABIPG9421C

..... क्रेता

रचियता :– ए0 के0 सैलवाल, एडवोकेट, विकासनगर जिला देहरादून।

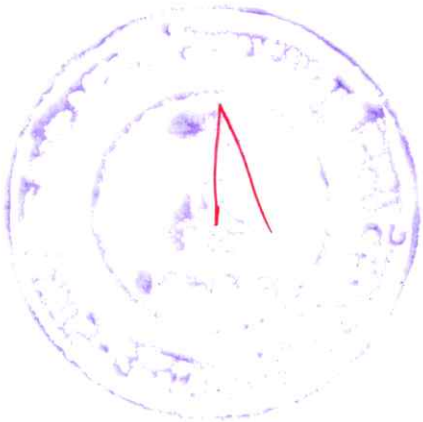

Online Public Data Entry Summary

UKPDE2023045217579

DISTRICT NAME :देहरादून SRO :

उत्तराखण्ड शासन UKPDE2023045217579 From 16 Feb 2023 10-Jul-2023 1:42:07PM

Appointment Date: Appointment Time: Appointment TokenNo:

Mutation Office तहसील विकासनगर

Deed/Article Type :Sale (Immovable)

Sub-Deed/Sub-Article :Sale(Residential Plot)

Village/Location For Index :धौलास -२.B-1 नंदा की चौकी से आमवाला मार्ग तक धौलास की सीमा समाप्ति तक

Village/Location/Road Selected for Circle RateList :धौलास -२.B-1 नंदा की चौकी से आमवाला मार्ग तक धौलास की सीमा समाप्ति तक

Khewat :

Khatoni :

Khasra :228, 229

House/Flat No:

Area :947.8000 वर्ग मीटर

Latitude 30.3890720000 Longitude 78.0086370000

Land Value :7,000,000.00 Construction Value :0.00

Transaction Value :7,000,000.00 Market Value :7,000,000.00

Advance :0.00 Lease Period :0.00 Avg. Rent :0.00

Stamp Duty :350,500.00 Regn Fees :25,000.00

Pasting Fees :100 Page :28

व्यवसायिक निर्माण का विवरण

क्र.सं	निर्माण का प्रकार	क्षेत्रफल

आवासीय निर्माण का विवरण

क्र सं	निर्माण क्षेत्र	निर्माण का प्रकार	निर्माण तल	ह्रास वर्ष	रक्का

निबंधक शुल्क का विवरण

क्र सं	भुगतान की विधि	धनराशि	संदर्भ क्रमांक
1	Cash	25,000.00	0

स्टाम्प शुल्क का विवरण

क्र सं	भुगतान की विधि	धनराशि	संदर्भ क्रमांक	जारी दिनांक	स्टांप विक्रेता आईडी
1	e-Stamp	350,500.00	0	10-Jul-2023	

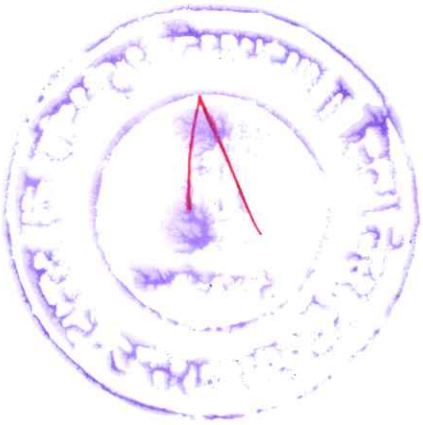

Appointment Date: Appointment Time: Appointment TokenNo:

Mutation Office तहसील विकासनगर

पक्षकारों का विवरण

पक्षकार का प्रकार	पक्षकार का विवरण	हस्ताक्षर	व्यवसाय	पैन नं	मोबाइल नं	पहचान पत्र संख्या
विक्रेता / प्रथम पक्ष	श्री राजेश कुमार बेलवाल पुत्र श्री रामचन्द्र बेलवाल निवासी एकता विहार सहस्त्रधारा रोड देहरादून		PRIVATE JOB	AJHPB5778N	0000000000	PAN CARD : AJHPB5778N
क्रेता / द्वितीय पक्ष	श्री श्याम कुमार गुजराल पुत्र श्री बी० एन० गुजराल निवासी ७९/१४ मुनिसिपल रोड डालनवाला देहरादून		PRIVATE JOB	ABIPG9421C	0000000000	PAN CARD : ABIPG9421C
गवाह	श्री संजय कुमार पुत्र श्री ज्योति राम निवासी जस्सोवाला विकासनगर देहरादून		PRIVATE JOB		0000000000	ADHAAR : 9697 6666 1774
गवाह	श्री विशाल कुमार पुत्र श्री कुलदीप कुमार निवासी डांडीपुर मोहल्ला देहरादून		PRIVATE JOB		0000000000	DL : UK-0720130278406

Seller Body Type : NA Purchaser Body Type: NA Permission Type: NA

Do not have Property above 250 sqr mt in any other location in Uttarkhand : NA

Land or Property holding in UK before 12-09-2003 : NA

Cersai Nill Report : View Cersai Report

Uploaded NEC / 12 years Khatoni Details : View NEC Report

NA Report : View Permission Report

Uploaded Khatoni for Seller : View Seller Khatoni

Uploaded Khatoni for Purchaser : View Purchaser Khatoni

Transaction Details : NA

Deed Writer /Advocate Name :A K SAILWAL

पछवादून बार ऐसोसिएशन

अप्रैल 2021 – मार्च 2022

विकासनगर, देहरादून (उत्तराखण्ड)

पुस्तकालय अनुदान

न0 41000 दिनांक.....

रू0. 200/-

अध्यक्ष पुस्तकालयाध्यक्ष सचिव

आयकर विभाग
INCOME TAX DEPARTMENT

भारत सरकार
GOVT. OF INDIA

स्थायी लेखा संख्या कार्ड
Permanent Account Number Card
AJHPB5778N

नाम / Name
RAJESH KUMAR BELWAL

पिता का नाम / Father's Name
RAM CHANDRA BELWAL

जन्म की तारीख / Date of Birth
24/05/1983

हस्ताक्षर / Signature

17102019

स्थाई लेखा संख्या /PERMANENT ACCOUNT NUMBER
ABIPG9421C

नाम /NAME
SHYAM KUMAR GUJRAL

पिता का नाम /FATHER'S NAME
BHOLA NATH GUJRAL

जन्म तिथि /DATE OF BIRTH
27-02-1959

हस्ताक्षर /SIGNATURE

आयकर आयुक्त, मेरठ
COMMISSIONER OF INCOME-TAX, MEERUT

भारत सरकार
Government of India



संजय कुमार
Sanjay Kumar
जन्म तिथि / DOB : 05/08/1975
पुरुष / Male

9697 6666 1774

आधार - आम आदमी का अधिकार

भारतीय विशिष्ट पहचान प्राधिकरण
आधार
Unique Identification Authority of India

पता:
संबोधित: ज्योति राम, वॉर्ड न . 2, जस्सोवाला, देहरादून, जस्सोवाला, उत्तराखंड, 248142

Address:
S/O: Jyoti Ram, ward no . 2, Jassowala, Dehradun, Jassowala, Uttarakhand, 248142

9697 6666 1774

1947
1800 300 1947

help@uidai.gov.in

www.uidai.gov.in

UNION OF INDIA Driving Licence

UK-0720130278406

Date of Issue
21-11-2013

Validity
(NT) 20-11-2033

Date of Birth
22-02-1994

Blood Group
Unknown

Name
VISHAL KUMAR

Father
KULDEEP KUMAR

UK-0720130278406

21.11.2013 21.11.2013

Mobile No.
******2600

Endorsement Date
07-12-2022

Endorsement No.
UK07 /DLD/0004757/2022

Present Address
206 DANDIPUR MOHALLA DEHRADUN
DEHRADUN 248001

Holder's Signature

Issuing Authority Sign
RTO, DEHRADUN

Form 7 Rule 16(2)

कार्यालय जिलाधिकारी देहरादून / जिला निबंधक देहरादून के पत्रांक 273 / मु0नि0लि0 / 2015 दिनांक 19 अगस्त 2015 यथासंशोधित पत्रांक संख्या 190 / मु0नि0लि0 / 2015 दिनांक 21 अगस्त 2015 के अनुपालन में।

उपनिबन्धक कार्यालय विकासनगर में पंजीकरण हेतु प्राप्त विलेख में अन्तरित भूमि / सम्पत्ति का स्थल फोटोग्राफ निष्पादित विलेख के दिनांक

दिनांक–10.07.2023
मौजा –धौलास
परगना– पछवादून जिला देहरादून

रकबा –947.80 वर्गमीटर



सत्यापित
हस्ताक्षर

सत्यापित
हस्ताक्षर



सत्यमेव जयते

INDIA NON JUDICIAL

Government of Uttarakhand

e-Stamp

Certificate No.	:	IN-UK62527425290074V
Certificate Issued Date	:	10-Jul-2023 03:21 PM
Account Reference	:	NONACC (SV)/ uk1210004/ VIKAS NAGAR/ UK-DH
Unique Doc. Reference	:	SUBIN-UKUK1210004311550536235 68V
Purchased by	:	SHYAM KUMAR GUJRAL
Description of Document	:	Article 23 Conveyance
Property Description	:	MAUZA DHAULAS, VIKASNAGAR, DEHRADUN
Consideration Price (Rs.)	:	70,00,000 (Seventy Lakh only)
First Party	:	RAJESH KUMAR BELWAL
Second Party	:	SHYAM KUMAR GUJRAL
Stamp Duty Paid By	:	SHYAM KUMAR GUJRAL
Stamp Duty Amount(Rs.)	:	3,50,500 (Three Lakh Fifty Thousand Five Hundred only)

अनिल कुमार सैनी
स्टाम्प विक्रेता
तहसील विकासनगर (दे०दून)

Please write or type below this line

JD 0039938231

Statutory Alert:

1. The authenticity of this Stamp certificate should be verified at 'www.shcilestamp.com' or using e-Stamp Mobile App of Stock Holding. Any discrepancy in the details on this Certificate and as available on the website / Mobile App renders it invalid.
2. The onus of checking the legitimacy is on the users of the certificate.
3. In case of any discrepancy please inform the Competent Authority.

Verified and Locked
Sub-Registrar-II
Vikasnagar

Warning

"The contents of this certificate can be verified and authenticated world-wide by any members of the public at www.shcilestamp.com or at any Authorised collection center address displayed at www.shcilestamp.com free of cost."

"Any alteration to this certificate renders it invalid. Use of an altered certificate without all the security features could constitute a criminal offence."

"This document contains security features like coloured background with Lacey Geometric Flexible patterns and Subtle Logo images, Complex ornamental design borders, Anti - copy text, the appearance of micro printing, artificial watermarks and other Overt and Covert features."



विक्रय – विलेख

श्री राजेश कुमार बेलवाल पुत्र श्री रामचन्द्र बेलवाल निवासी– एकता विहार सहस्त्रधारा रोड देहरादून, उत्तराखण्ड।(जिनको इस विक्रय विलेख में आगे सुगमता एवम सुविधा एवं संक्षिप्तता की दृष्टि से **"विक्रेता"** के रूप में सम्बोधित किया है।)

.....विक्रेता

ने

श्री श्याम कुमार गुजराल पुत्र श्री बी0एन0 गुजराल निवासी–79/14 मुनिसिपल रोड डालनवाला जिला देहरादून।(जिनको इस विक्रय विलेख में आगे सुगमता एवम सुविधा एवं संक्षिप्तता की दृष्टि से **"क्रेता"** के रूप में सम्बोधित किया है।)

.....क्रेता

के पक्ष में अंकित व निष्पादित किया।

विदित हो कि विक्रयपत्र की सूची में वर्णित भूमि हर प्रकार के भार, बंधन, न्यायालय, बैंक, सहकारी समिति अथवा अन्य किसी वित्तीय संस्था की बंधक, ऋण बन्धन, प्रतिभूमि कुर्की से मुक्त व स्वच्छ हस्तान्तरण योग्य स्वामित्व की भूमि है विक्रेता द्वारा ऐसा कोई कार्य विक्रय अनुबन्ध आदि अन्य किसी व्यक्ति से नहीं किया हुआ है जिससे इस भूमि के अन्तरण में किसी प्रकार की बाधा हो।

विदित हो कि सूची में वर्णित भूमि विक्रेता ने इसके पूर्व स्वामी श्री रणधीर सिंह वर्मा पुत्र श्री सुचेत सिंह वर्मा निवासी–रोचीपुरा निरंजनपुर देहरादून से पंजीकृत विक्रय पत्र के माध्यम से क्रय की हुई है जिसका पंजीयन उपनिबन्धक कार्यालय प्रथम विकासनगर के यहां बही सं0–1 जिल्द 6817 पृष्ठ 165/186 क्रमांक 1635 दिनांक 10.02.2023 को विधिवत दर्ज व अंकित है तथा श्री रणधीर सिंह वर्मा का नाम राजस्व अभिलेखों में फसली वर्ष 1414 से बतौर संक्रमणीय भूमिधर दर्ज व अंकित चला आ रहा है।

विदित हो कि विक्रेता ने विक्रीत भूमि को बिना किसी बहकावे, सिखलावे बिना किसी अनुचित दबाव के क्रेता उपरोक्त को **मु0 70,00,000/–(सत्तर लाख रूपये)** में विक्रय कर दिया है जिसके अनुपालन में यह विक्रय पत्र अंकित व निष्पादित किया जा रहा है।

अत : यह विक्रय–विलेंख पूर्ण स्पष्टीकरण हेतु निम्न दर्शाता है :–

1. यह कि विक्रेता ने क्रेता से विक्रय मूल्य / प्रतिफल मु0 70,00,000 / –(सत्तर लाख रूपये) निम्न प्रकार से प्राप्त कर लिये हैं–

   क. मु0–50,00,000 / –रू0 द्वारा RTGS-BDBLR52023071000001111 दिनांक 10.07.2023

   ख. मु0–19,30,000 / –रू0 द्वारा चैक सं0–000039 बंधन बैंक देहरादून दिनांक 10.07.2023

   ग. मु0–70,000 / –रू0 द्वारा TDS के माध्यम से दिनांक 10.07.2023 को अदा कर दिये गये हैं।

   जिसकी प्राप्ति की अभिस्वीकृति विक्रेता उपनिबन्धक विकासनगर देहरादून के समक्ष स्वीकार करता है। अब विक्रीत सम्पत्ति की बाबत कुछ भी लेन–देन दोनो पक्षो के मध्य शेष नही रहा है। विक्रय मूल्य के रूप मे कोई राशि शेष नही रह गई हैं।

2:– यह कि विक्रेता ने क्रेता को स्थल पर जाकर, विक्रीत भूमि से अपना अध्यासन हटाकर भूमि का रिक्त एवम् वास्तविक अध्यासन क्रेता को सौंपकर अपने समतुल्य अध्यासित कर आरूढ करा दिया है। इस प्रकार क्रेता ने विक्रीत भूमि का अध यासन प्राप्त कर लिया है।

3:– यह कि विक्रीत भूमि स्वच्छ अन्तरण योग्य स्वामित्व की भूमि है। यदि विक्रेता के किसी स्वामित्व व अधिकार दोष अथवा किसी अन्य दोष के कारण, क्रेता विक्रीत भूमि अथवा इसके किसी भाग के अध्यासन अथवा स्वामित्व से वंचित हो जाये तो ऐसी परिस्थिति में क्रेता को यह अधिकार होगा कि वह निकले हुये भू–भाग की कीमत मय हर्जे खर्चे सहित विक्रेता की चल अचल सम्पत्ति से जिस प्रकार चाहे वसूल कर लेवे, इसमें विक्रेता व उसके किसी उत्तराधिकारी व वारिस को आपत्ति करने का अधिकार नही होगा।

4:– यह कि विक्रेता, क्रेता के साथ नामान्तरण की कार्यवाही में पूर्ण सहयोग प्रदान करेगा। क्रेता को अधिकार होगा कि वह राजस्व अभिलेखों से विक्रेता का नाम विक्रीत भूमि से निरस्त कराकर अपना नाम बतौर मालिक, स्वामी दर्ज करा लेवे और इसके लिये यदि विक्रेता के किसी लेख, विलेख, शपथपत्र आदि की आवश्यकता हुई तो विक्रेता यह सब कार्यवाही करने हेतु सदैव तैयार व पाबंद रहेगा, जिसका खर्च क्रेता स्वयं वहन करेगा।

5:– यह कि विक्रीत भूमि में वास्ते मालिकाना, रास्ता, नाली, हवा, पानी रोशनी सुखाधिकार आदि के बाबत जो अधिकार विक्रेता को आज की तिथि तक प्राप्त है तथा भविष्य में प्राप्त होने सम्भव हो, उन सबका मालिक आज की तिथि से क्रेता हो गया है।

बही संख्या 1 रजिस्ट्रीकरण संख्या 5[illegible]12 वर्ष 2023

Sale (Immovable)
Sale(Residential Plot)

प्रतिफल रु0 : 7,000,000.00
मालियत रु0 : 7,000,000.00

रजिस्ट्रेशन शुल्क	प्रतिलिपि शुल्क	इलेक्ट्रानिक प्रोसेसिंग शुल्क	कुल योग	शब्द लगभग
रु0 25,000.00	रु0 100.00	रु0 240.00	रु0 25,340.00	1,000

श्री श्याम कुमार गुजराल पुत्र श्री बी० एन० गुजराल निवासी ७९/१४ मुनिसिपल रोड डालनवाला देहरादून ने आज दिनांक 10 Jul 2023 समय मध्य 3PM व 4PM को कार्यालय उपनिबन्धक विकासनगर द्वितीय मे प्रस्तुत किया ।

श्याम कुमार गुजराल

उपनिबन्धक
विकासनगर द्वितीय
10-Jul-2023

इस लेख पत्र का निष्पादन विलेख मे लिखित तथ्यों को सुन व समझकर श्री राजेश कुमार बेलवाल पुत्र श्री रामचन्द्र बेलवाल निवासी एकता विहार सहस्त्रधारा रोड देहरादून \ ने विक्रय धन मुबलिग रु0 7,000,000.00 प्रलेखानुसार पाकर निष्पादन स्वीकार किया । इस लेखपत्र का निष्पादन क्रेता श्री श्याम कुमार गुजराल पुत्र श्री बी० एन० गुजराल निवासी ७९/१४ मुनिसिपल रोड डालनवाला देहरादून \ ने भी स्वीकार किया ।

जिनकी पहचान श्री संजय कुमार पुत्र श्री ज्योति राम निवासी जस्सोवाला विकासनगर देहरादून तथा श्री विशाल कुमार पुत्र श्री कुलदीप कुमार निवासी डांडीपुर मोहल्ला देहरादून ने की।

उपनिबन्धक
विकासनगर द्वितीय
10-Jul-2023

6:— यह कि इस विक्रयपत्र में प्रयुक्त शब्द विक्रेता एवं क्रेता से आशय उनके वारिसान, हित प्रतिनिधि स्थानापन्न से भी है।

वांछित — विवरण

1:— यह कि विक्रीत भूमि नगर पालिका, नगर पंचायत के अन्तर्गत स्थित नहीं है तथा औद्योगिक क्षेत्र से बाहर है तथा विक्रीत भूमि मुख्य चकराता रोड से 8 किमी से अधिक दूर तथा नन्दा की चौकी से आमवाला मार्ग पर धौलास की सीमा समाप्ति तक 51 मीटर से अधिक दूर स्थित है।

2:— यह कि विक्रेता/क्रेता अनुसूचित जाति व जन जाति से सम्बन्धित नहीं है तथा दोनों भारतीय नागरिक है।

3:— यह कि विक्रीत भूमि पर कोई बाग, पेड, निर्माण आदि नही है।

4:— यह कि विक्रीत भूमि की बाबत् पक्षकारों के मध्य पूर्व में कोई पंजीकृत इकरारनामा नहीं हुआ हैं।

5:— यह कि विक्रीत भूमि की सर्किल दर श्रीमान कलेक्टर महोदय, देहरादून द्वारा मु0 7000/—रूपये प्रति वर्गमीटर निर्धारित है तथा विक्रीत भूमि में 5 मीटर से अधिक व 12 मीटर से कम चौडा रास्ता होने के कारण 5 प्रतिशत अतिरिक्त वृद्धि के उपरान्त भूमि की कुल मालियत मु0—70,00,000/—रू0 होती है जिस पर नियमानुसार 5% की दर से मु0 3,50,500/—रूपये का स्टाम्प शुल्क अदा किया जा रहा है।

6:— यह कि यह कि विक्रीत भूमि ग्रामीण सीलिंग की धारा 6(2) से व चाय बागान की लाभान्वित भूमि नहीं है।

7:— यह कि विक्रीत भूमि नदी, ढांग, बंजर, धार्मिक संस्थान व ट्रस्ट इत्यादि की भूमि नही है।

8:— यह कि विक्रीत भूमि गोल्डन फोरेस्ट व पी0ए0सी0एल0 कम्पनी व अन्य सहयोगी कम्पनी से सम्बन्धित नहीं है तथा वाद विवाद से पूर्णतयः मुक्त है।

9:— यह कि विक्रीत भूमि सर्वाधिकार, सुखाधिकार सहित विक्रय की गयी है।

10:— यह कि विक्रीत भूमि नदी, ढांग, बंजर, खाला आदि की भूमि नहीं है।

11:— यह कि क्रेता /परिवार के नाम पर उत्तराखण्ड में 2003 से पूर्व भूमि है इस कारण क्रेता द्वारा भूमि क्रय करने में (उत्तरांचल राज्य) उ0 प्र0 जमींदारी विनाश अधिनियम 1950 (अनुकूलन एवं रूपान्तरण आदेश 2001) (संशोधित) अधिनियम 2003/(संशोधित) अधिनियम 2007 के अन्तर्गत पूर्ण रूप से सक्षम है।

12:— यह कि कि "क्रेता/विक्रेता या उभयपक्ष विदेशी नागरिक नहीं है तथा विदेशों में रह रहे भारतीय मूल के नहीं है, इसके अतिरिक्त उभयपक्ष पाकिस्तान, बांग्लादेश, श्रीलंका, अफगानिस्तान, चीन, ईरान, नेपाल, भूटान के नागरिक नहीं है तथा वहां निवास कर रहे भारतीय मूल के नहीं है।

बही संख्या 1 रजिस्ट्रीकरण संख्या 5812 वर्ष 2023

राजेश कुमार बेलवाल | श्याम कुमार गुजराल | संजय कुमार | विशाल कुमार

प्रतिज्ञ एवं साक्षीगण भद्र प्रतीत होते हैं। सभी के अंगुष्ठ चिन्ह नियमानुसार लिये गये है।

रजिस्ट्रीकर्ता अधिकारी /
उप-निबंधक, विकासनगर द्वितीय
10 Jul 2023

13:– यह कि विक्रीत भूमि टी0एच0डी0सी0 विस्थापित क्षेत्र से बाहर है।

14 :– यह कि प्रश्नगत अन्तरित सम्पत्ति रियल इस्टेट रेग्लूशेन एंड डेवलमेंट एक्ट 2016 एंव यशा प्रख्यापित उत्तराखण्ड रियल इस्टेट रेग्लूशेन एंड डेवलमेंट एक्ट 2016 (जनरल) रूल्स 2017 के अन्तर्गत परिभाषित रियल इस्टेट में किसी प्रोजेक्ट के अन्तर्गत आच्छादित नहीं है चूंकि विक्रय की जा रही सम्पत्ति विक्रेता की व्यक्तिगत निजी सम्पत्ति है एंव विक्रेता की भूमि किसी भी ग्रुप हाउसिंग, मिक्सड डेवलेपमेंट प्रोजेक्टस अथवा प्लाटेड डेवलमेंट प्रोजेक्टस से आछादित न होने के कारण रेरा एक्ट के अन्तर्गत प्राविधानित नियमों के अनुसार पंजीकरण की आवश्यकता नहीं है अतः उक्त सम्पत्ति को विक्रय किये जाने में किसी भी प्रकार का रेरा एक्ट का उल्लघंन विक्रेता द्वारा नहीं किया जा रहा है।

15 :– यह कि विक्रीत भूमि का अक्षान्तर–30.389072 व देशान्तर–78.008637 है।

विवरण विक्रीत– भूमि

भूमि खसरा सं0–228 रकबा 501.85 खसरा नं0–229 रकबा 445.95 वर्गमीटर कुल रकबा 947.80 वर्गमीटर अर्थात 1133.14 वर्गगज स्थित मौजा धौलास, तहसील विकासनगर, परगना पछवादून, जिला देहरादून, उत्तराखण्ड। जिसकी सीमायें निम्न प्रकार हैं व मानचित्र सलंग्न है–

पूरब	–	भूमि अन्य
पश्चिम	–	भूमि अन्य
उत्तर	–	भूमि अन्य
दक्षिण	–	25 फुट चौडा रास्ता।

समस्त सर्वाधिकार व सुखाधिकार सहित

अतः यह विक्रय पत्र आज दिनांक 10.07.2023 को स्थान विकासनगर, जिला देहरादून में अंकित कर दिया गया है ताकि सनद रहे वक्त जरूरत काम आवे।

रजिस्ट्रेशन अधिनियम 1908 की धारा 32–ए के अनुपालन हेतु फिंगर प्रिंटस

दांये हाथ (Right Hand) की अंगुलियों के चिन्ह्

अंगुष्ठ तर्जनी मध्यमा अनामिका कनिष्ठका

बांये हाथ (Left Hand) की अंगुलियों के चिन्ह्

अंगुष्ठ तर्जनी मध्यमा अनामिका कनिष्ठका

ह0 विक्रेता .....

दांये हाथ (Right Hand) की अंगुलियों के चिन्ह्

अंगुष्ठ तर्जनी मध्यमा अनामिका कनिष्ठका

बांये हाथ (Left Hand) की अंगुलियों के चिन्ह्

अंगुष्ठ तर्जनी मध्यमा अनामिका कनिष्ठका

ह0 क्रेता .....

साक्षी :–
1.....
श्री संजय कुमार
पुत्र श्री ज्योति राम
निवासी–जस्सोवाला विकासनगर
जिला देहरादून।
UID- 9697 6666 1774

साक्षी :–
2.....
श्री विशाल कुमार
पुत्र श्री कुलदीप कुमार
निवासी–डांडीपुर मौहल्ला
देहरादून।
DL No- UK-0720130278406

रचियताः– ए0 के0 सैलवाल, एडवोकेट, विकासनगर जिला देहरादून।

बही संख्या 1 जिल्द 5,266 के पृष्ठ 377 से 400 पर क्रमाक 5812

पर आज दिनांक 10 Jul 2023 को रजिस्ट्रीकरण किया गया।

रजिस्ट्रीकर्ता अधिकारी /
उप-निबंधक,विकासनगर द्वितीय
10 Jul 2023

मानचित्र

विक्रेता–श्री राजेश कुमार बेलवाल पुत्र श्री रामचन्द्र बेलवाल निवासी– एकता विहार सहस्त्रधारा रोड देहरादून, उत्तराखण्ड।

क्रेता–श्री श्याम कुमार गुजराल पुत्र श्री बी0एन0 गुजराल निवासी–79/14 मुनिसिपल रोड डालनवाला जिला देहरादून।

विवरण भूमि–भूमि खसरा सं0–228 रकबा 501.85 खसरा नं0–229 रकबा 445.95 वर्गमीटर कुल रकबा 947.80 वर्गमीटर अर्थात 1133.14 वर्गगज स्थित मौजा धौलास, तहसील विकासनगर, परगना पछवादून, जिला देहरादून, उत्तराखण्ड।

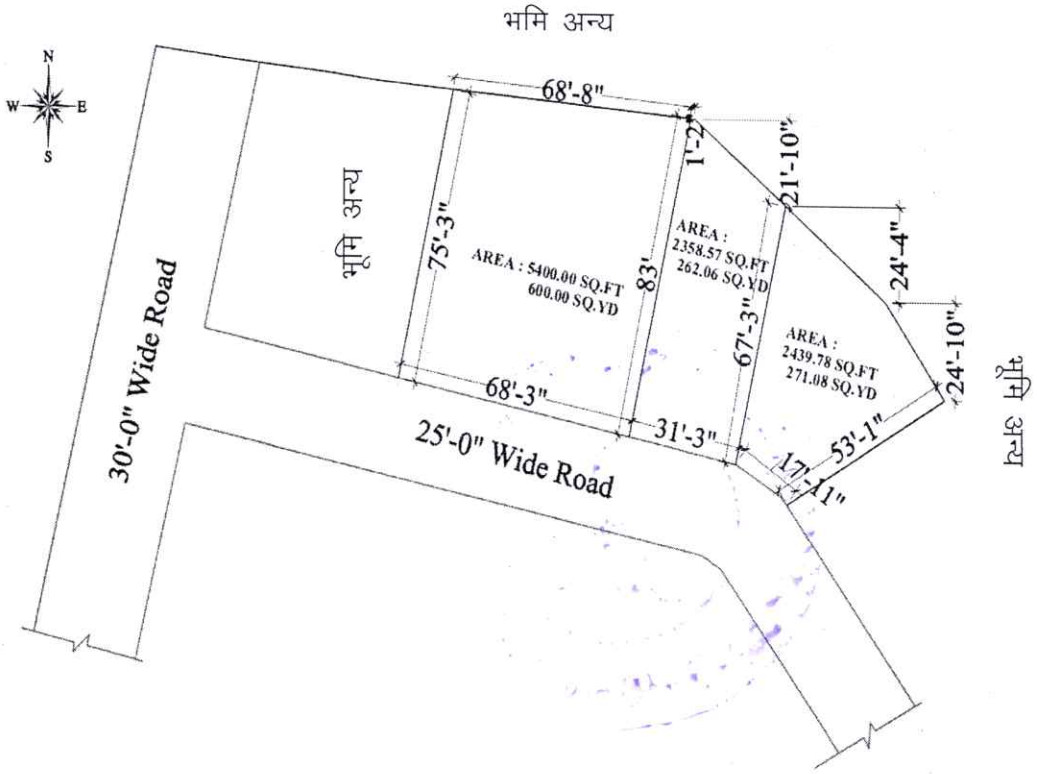

ह0 विक्रेता .....

ह0 क्रेता.....

बही संख्या 1 जिल्द 5,266 के पृष्ठ 377 से 400 पर क्रमाक 5812

पर आज दिनांक 10 Jul 2023 को रजिस्ट्रीकरण किया गया।

रजिस्ट्रीकर्ता अधिकारी /
उप-निबंधक,विकासनगर द्वितीय
10 Jul 2023